1391. 检查网格中是否存在有效路径

难度: **Medium**

给你一个 *m* x *n* 的网格 `grid` 。网格里的每个单元都代表一条街道。 `grid[i][j]` 的街道可以是：

- **1** 表示连接左单元格和右单元格的街道。
- **2** 表示连接上单元格和下单元格的街道。
- **3** 表示连接左单元格和下单元格的街道。
- **4** 表示连接右单元格和下单元格的街道。
- **5** 表示连接左单元格和上单元格的街道。
- **6** 表示连接右单元格和上单元格的街道。

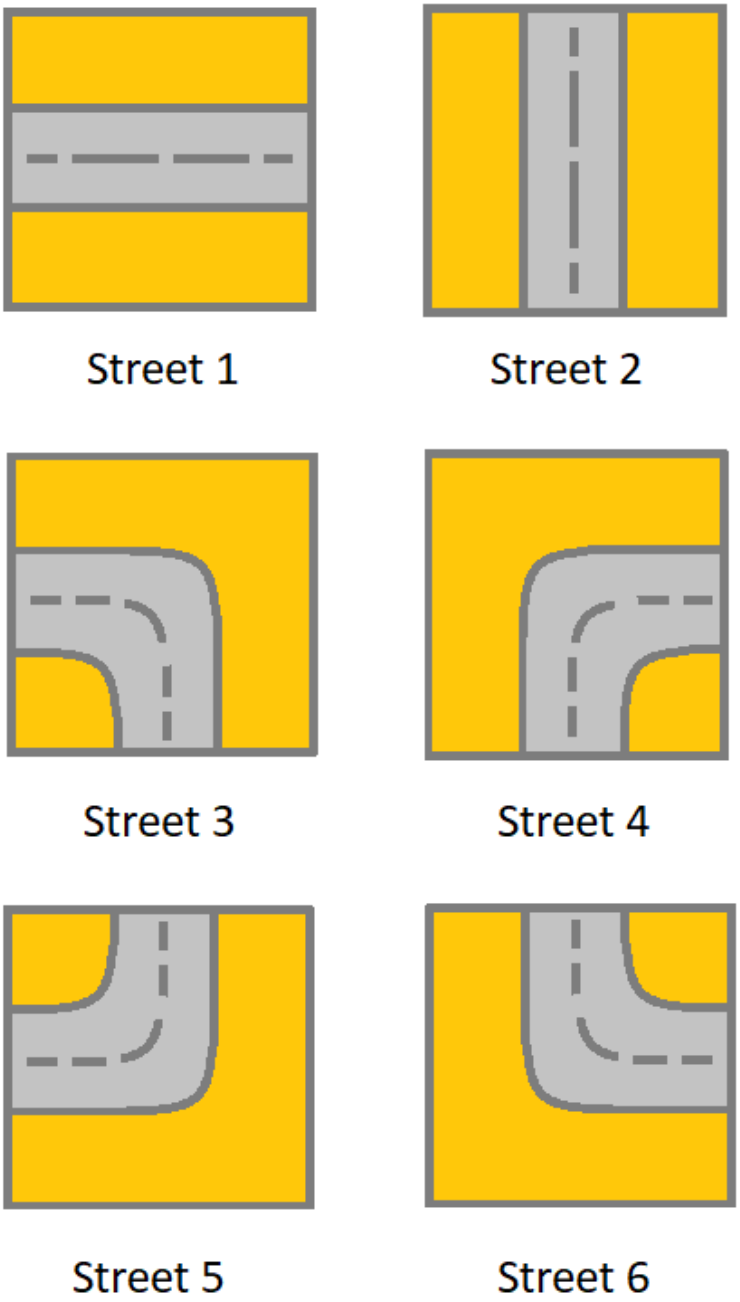

你最开始从左上角的单元格 `(0,0)` 开始出发，网格中的「有效路径」是指从左上方的单元格 `(0,0)` 开始、一直到右下方的 `(m-1,n-1)` 结束的路径。**该路径必须只沿着街道走**。

注意：你 **不能** 变更街道。

如果网格中存在有效的路径，则返回 `true` ，否则返回 `false` 。

示例 1：



```
输入：grid = [[2,4,3],[6,5,2]]
输出：true
解释：如图所示，你可以从 (0, 0) 开始，访问网格中的所有单元格并到达 (m - 1, n - 1) 。
```

示例 2：

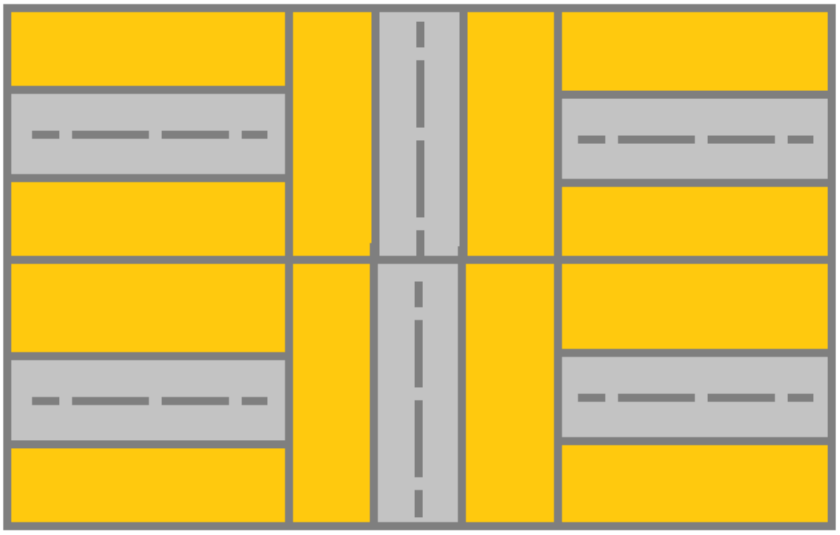

```
输入：grid = [[1,2,1],[1,2,1]]
输出：false
解释：如图所示，单元格 (0, 0) 上的街道没有与任何其他单元格上的街道相连，你只会停在 (0, 0) 处
```

示例 3：

```
输入：grid = [[1,1,2]]
输出：false
```

解释：你会停在 (0, 1)，而且无法到达 (0, 2) 。

示例 4：

```
输入：grid = [[1,1,1,1,1,1,3]]
输出：true
```

示例 5：

```
输入：grid = [[2],[2],[2],[2],[2],[2],[6]]
输出：true
```

提示：

- m == grid.length
- n == grid[i].length
- 1 <= m, n <= 300
- 1 <= grid[i][j] <= 6